地形

* 地形的2大力量：內營力 / 外營力

1. 內營力

(1) 板塊作用：地球內部的熱對造成的板塊作用

a. 海陸相對關係 < 離水作用：陸地相對於海平面上升　ex. 大陸島形成
沉水作用：〃　下降

b. 板塊作用 < 聚合：形成火山、新的山脈
張裂：形成峽谷、裂谷

c. 地形的新舊 < 老：平坦、礦產多
年輕：崎嶇

* 山脈的新舊 < 古褶曲山脈：平坦
新褶曲山脈：崎嶇，多地震、火山運動

* 環太平洋火山地震帶

(2) 火山作用

a. 作用方式 < 侵入作用：岩漿侵入地表
噴出作用：岩漿噴出地表

噴出作用 → 1. 猛烈式：酸性岩漿、黏度大　常見地形：火山錐、火山口(火口湖)
2. 寧靜式：基性岩漿、〃小　常見地形：熔岩台地、熔岩高原

b. 火山對環境的好處：火山土可以帶來肥沃土地

2. 外營力

(1) 風化作用：地表岩石受氣候/生物作用，在原地崩解/分解的過程　ex. 單岩(差別風化)、棒狀岩

1. 物理風化：乾冷地區好發（主因：水的凍脹、熱脹冷縮）
↳ 凍脹作用
2. 化學風化：溼熱地區好發（高溫多雨）

(2) 崩壞作用：風化物質受重力/水分，由高向低的移動過程　ex. 潛移(慢)、土石流、地滑、山崩(快)

好發條件：水多、坡度大、岩層質地鬆散

(3) 侵蝕、搬運、堆積：詳細在河流地形

河流地形：受河水由高向低移動，產生侵蝕、搬運、堆積

* 演習：侵蝕 vs. 搬運 vs. 堆積 (坡度、流速、流量、粒徑大小、上中下游、河道寬度)

1. 侵蝕

依形式分成：沖蝕、磨蝕、溶蝕

依方向分：下蝕(加深)、側蝕(加寬)、向源侵蝕(加長)

(1) 侵蝕基準面：侵蝕的最低界限 (最終侵蝕基準面)

↳ 海平面相對陸地下降 → 基準面下降 → 侵蝕力量↑


* 區部時侵蝕基準面：河川消失

其他：河灣作用、壺穴、瀑布、差異侵蝕

2. 堆積作用

(1) 淘選度：顆粒大的比較先沉積(較上游)，較小的較慢沉積(較下游)

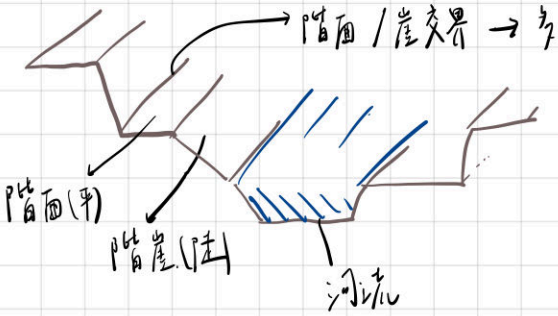
(2) 沖積扇 vs. 三角洲 (差異是分布地區不同，成因都是堆積)



3. 其他：河流發展階段、侵蝕輪迴




4. 河階地形（堆積＋侵蝕）：河床不斷被河水向下侵蝕，形成台狀階層



等高線判斷：河道兩側出現疏密不均
- 疏 → 階面
- 密 → 階崖


5. 曲流地形：河流彎彎曲曲的



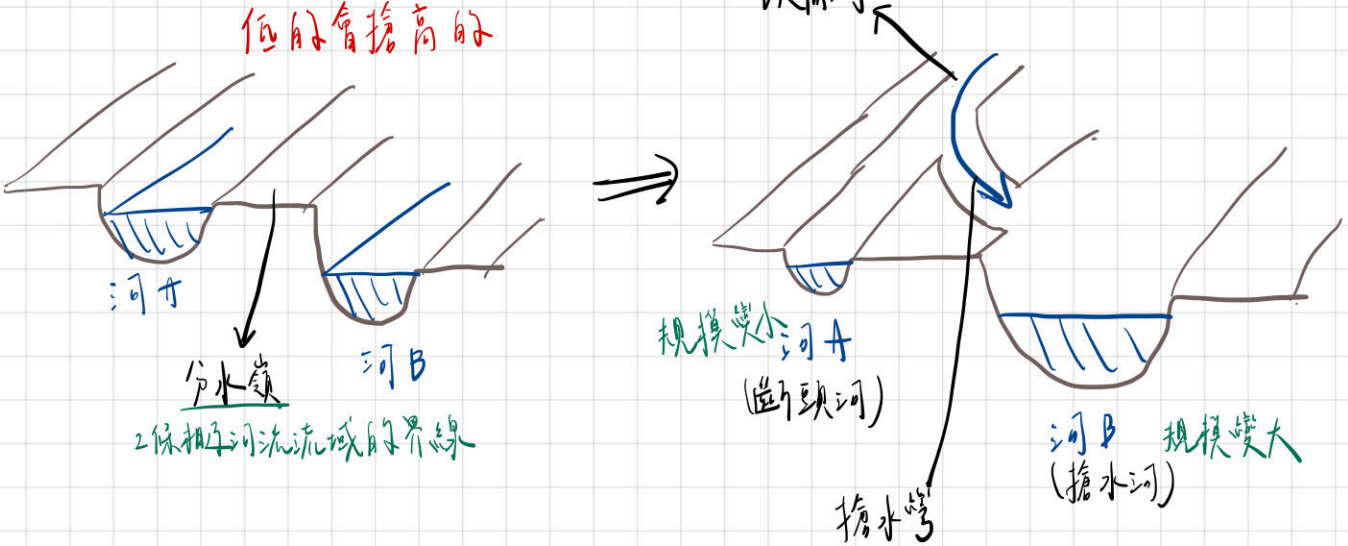
凸岸（滑走坡）：堆積／流速慢／淺／前移

凹岸（侵蝕坡）：侵蝕／流速快／深／禁合居住／設堤

* 左、右岸：上游往下游看，左邊就是左岸，反之
* 牛軛湖：



6. 搶水地形



成因：低位河（河B）向源／側向侵蝕，切穿分水嶺，把高位河（河A）的河水搶水